Descubre DAGUA

Donde la historia y la naturaleza se encuentran

DAGUA
MÁGICA Y BIODIVERSA

ALCALDÍA MUNICIPAL
DE DAGUA

Descubre DAGUA

Donde la historia y la naturaleza se encuentran

Ubicado en el corazón del Valle del Cauca, Dagua es un municipio que combina historia, cultura y biodiversidad en un entorno de ensueño. Decretado municipio en 1909 por la Compañía Constructora del Ferrocarril del Pacífico, este destino único se extiende entre Cali y Buenaventura, en un punto estratégico que conecta los Andes con el Pacífico.

Sus paisajes, atravesados por ríos majestuosos como el Dagua y el Anchicayá, ofrecen desde cálidos valles hasta frescas montañas envueltas en niebla. Aquí, el aroma del quereme, una flor nativa con propiedades mágicas y medicinales, se mezcla con el dulce sabor de la piña, el producto insignia de la región.

Dagua es historia viva: sus caminos fueron testigos de la ruta colonial hacia el mar y su legado cultural incluye el pandebono, un ícono de la gastronomía vallecaucana. Este rincón encantador invita a los viajeros a sumergirse en su riqueza natural, a recorrer sus senderos y a dejarse envolver por el amor y la hospitalidad de su gente.

¡Ven a Dagua y vive la magia del Valle del Cauca!

DAGUA
MÁGICA Y BIODIVERSA

DAGUA 1909
ALCALDÍA MUNICIPAL
DE DAGUA

Descubre DAGUA

Donde la historia y la naturaleza se encuentran

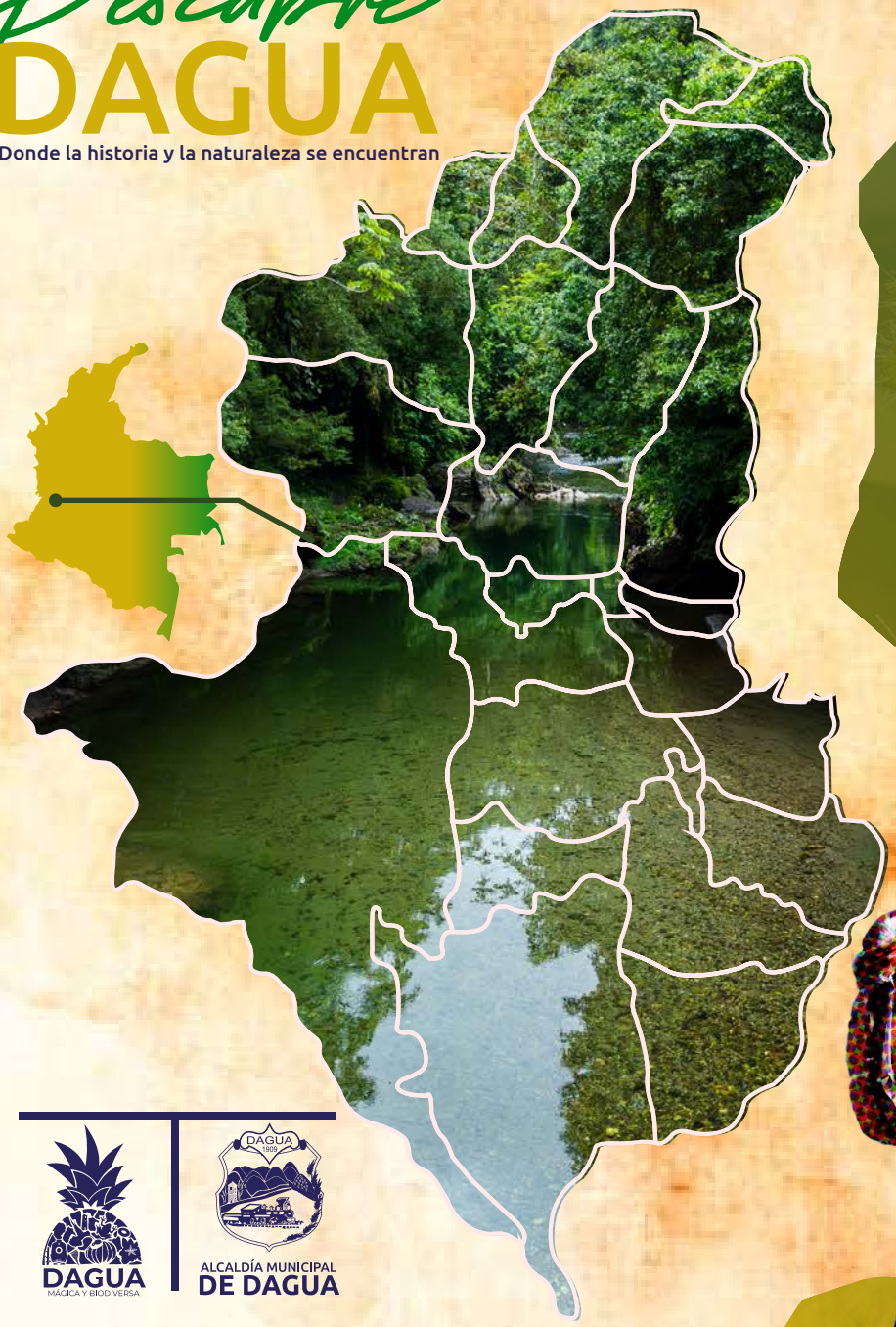

Dagua, el tercer municipio más grande del Valle del Cauca, se extiende entre las imponentes montañas de la Cordillera Occidental de los Andes. Este territorio, de 886 km², abarca desde los Farallones de Cali hasta los cerros de Clorinda y Palo Alto, ofreciendo una diversidad paisajística única.

Con un ecosistema que incluye el Enclave Subxerofítico del Dagua, sus áridos parajes albergan cactus endémicos como el Melocactus Curvispinus sub-especie Loboguerrero y la Opuntia bella, además de una rica fauna con más de 100 especies de aves. Este enclave natural representa el 70% de su área y es un testimonio de la adaptación de la vida en condiciones extremas.

Municipio:	Dagua
Gentilicio:	Dagüeño-Dagüeña
Peajes:	Cero
Población:	36,400
Temperatura a (°C):	Entre 14 y 25 °C
Distancia de Cali:	1 hora y 30 minutos

Ubicación Geográfica

DAGUA MÁGICA Y BIODIVERSA

ALCALDÍA MUNICIPAL DE DAGUA

Índice

Presentación DAGUA — Pag. 2-3

Oferta Turística

- Charco Guzmán — Pag.6
- Atuncela — Pag.7-8
- Dagua — Pag.9
- El Carmen — Pag.10
- KM 18 — Pag.11
- San José del Salado — Pag.12
- El Queremal — Pag.13
- Anchicayá — Pag.14
- Avistamiento de Aves Doña Dora — Pag.15
- Cascada Virgen de los Remedios — Pag.16
- Cascada el Manto de la Virgen — Pag.17
- Cascada La Elsa — Pag.17
- Charco La Oculta — Pag.18
- Siete Charcos — Pag.18
- Reserva Natural El Paraíso — Pag.19
- Charco La Sirena — Pag.20

Mapa Ruta Turística — Pag.21

Créditos — Pag.22

DAGUA
MÁGICA Y BIODIVERSA

ALCALDÍA MUNICIPAL DE DAGUA

Descubre DAGUA

Donde la historia y la naturaleza se encuentran

Descubre DAGUA

Donde la historia y la naturaleza se encuentran

Un lugar biodiverso por descubrir

Andinobates Bombetes

DAGUA
MÁGICA Y BIODIVERSA

ALCALDÍA MUNICIPAL
DE DAGUA

Charco Guzmán

Es un encantador lugar ubicado en el río Pepitas, en el corregimiento de Juntas Dagua, cercano a Cisneros, en la vía hacia el mar. Este lugar ofrece una inmersión total en la naturaleza del Pacífico, donde podrás disfrutar de caminatas a lo largo del río, y refrescantes baños en sus aguas.

Ofrece opciones de hospedaje cómodas y la posibilidad de contemplar paisajes impresionantes. No dejes pasar la oportunidad de degustar la exquisita gastronomía local, que complementa esta experiencia única en un entorno privilegiado.

DAGUA
MÁGICA Y BIODIVERSA

ALCALDÍA MUNICIPAL
DE DAGUA

Es un destino único en el mundo que te invita a explorar su excepcional biodiversidad en un entorno subxerofítico. Aquí, podrás disfrutar de caminatas guiadas por intérpretes ambientales que te mostrarán especies exclusivas de cactus, como el Melocactus Curvispinus sub-especie Loboguerrero, y te presentarán una variedad de aves hermosas que habitan la región.

Una de las actividades más populares es aprender sobre el proceso de elaboración de la panela a través de visitas guiadas por los locales y sus tradicionales trapiches. Sin duda, es un lugar donde la naturaleza y las investigaciones ambientales se entrelazan para ofrecerte una experiencia inolvidable, además este lugar te conectara con la Hacienda Santa Inés ubicada a pocos kilómetros donde podrás disfrutar de una variedad de actividades de recreación y pesca.

Atuncela



DAGUA
MÁGICA Y BIODIVERSA

ALCALDÍA MUNICIPAL
DE DAGUA

Actividades

Caminata, interpretación ambiental, avistamiento de aves, anfibios y flora.

Duración de la experiencia

10 horas.

Servicios Incluidos

Guianza – intérprete. Tarjeta de asistencia médica y bono ambiental.

Contacto

Turisteando Atuncela
WhatsApp: 321 8594016

Ruby Topaz Hummingbird

Producción de panela - El Trapiche Atuncela

Melocactus Curvispinus sub-especie Loboguerrero

Es el principal centro poblado de la región, donde su clima privilegiado ofrece experiencias únicas, como las piscinas de agua natural y una rica oferta agrícola. Este municipio, clave en la historia económica del Valle del Cauca, destaca por su línea férrea y su estación principal de tren, que narran su valioso legado histórico. Los visitantes pueden disfrutar también de la deliciosa gastronomía local, siendo el Encocado de Nayo uno de los platos más sabrosos, preparado con un pez nativo del río Dagua. Pasear por sus laderas permite una conexión auténtica con la naturaleza, la cultura local y la sabrosura de la rumba dagüeña.

Dagua



El Carmen

El Carmen es un encantador rincón de Dagua que se ha destacado en la mejora de las prácticas culinarias y gastronómicas de la región. Aquí, encontrarás una amplia variedad de establecimientos gastronómicos que ofrecen sabores auténticos de la cocina tradicional, conectándote con las ricas tradiciones culinarias del municipio.

El Carmen te ofrece opciones de hospedaje y piscinas de agua natural, destacando Las Chorreras del Carmen, un lugar que te sorprenderá con el poder del agua como símbolo de pureza y renovación. Disfruta de la serenidad de este lugar mientras te deleitas con su oferta gastronómica y natural.

DAGUA
MÁGICA Y BIODIVERSA

ALCALDÍA MUNICIPAL
DE DAGUA

KM 18

Este encantador lugar se destaca por su clima, que permite a los visitantes disfrutar de un rápido cambio entre la calidez y la frescura. El kilómetro 18 es un destino ideal para el avistamiento de aves en el bosque de niebla, donde podrás maravillarte con la rica biodiversidad característica de este ecosistema.

La zona ofrece una exquisita variedad gastronómica en sus establecimientos, que comparten territorio con la ciudad de Santiago de Cali. Entre las delicias recomendadas se encuentran los sabrosos asados, acompañados de reconfortantes bebidas calientes como la aguapanela con queso y el delicioso canelazo, un vino caliente que hará aún más placentera tu visita.

San José del Salado



San José del Salado es un encantador corregimiento que alberga una historia singular, destacando su emblemática Torre Mudéjar, un monumento católico de gran relevancia que data de 1770. Este pequeño y acogedor destino es perfecto para quienes buscan un lugar de descanso en sus fincas de veraneo.

San José del Salado actúa como un punto de conexión hacia otros lugares cercanos, como la Hacienda del Bono, donde podrás descubrir la rica historia detrás del famoso pandebono, uno de los amasijos más populares del mundo. Sumérgete en la cultura y la tradición de esta región del Valle del Cauca mientras disfrutas de su tranquilidad.

El Queremal

Descubre uno de los centros poblados más encantadores del municipio de Dagua, donde las artesanías, la tranquilidad y la cultura se entrelazan en un ambiente acogedor. En El Queremal, tendrás la oportunidad de disfrutar de la exquisita gastronomía y la calidez de sus habitantes. Sumérgete en las narrativas locales sobre la flor del quereme y su mágica reputación como símbolo de enamoramiento. Además, podrás relajarte en los charcos de agua templada y cristalina, convirtiendo a El Queremal en el lugar ideal para descansar y conectar con los atractivos de la cuenca de Anchicayá. ¡Un destino perfecto para disfrutar de la naturaleza y la cultura de la región!

DAGUA
MÁGICA Y BIODIVERSA

ALCALDÍA MUNICIPAL
DE DAGUA

Anchicayá es un paraíso megadiverso donde la naturaleza se muestra en todo su esplendor. Este destino, que conecta Dagua con Buenaventura, alberga ríos cristalinos, imponentes cascadas como "La Sirena" y lugares mágicos como "Siete Charcos", además de una rica biodiversidad con especies únicas de flora y fauna.

La comunidad local ha transformado su entorno a través del turismo sostenible, dejando atrás prácticas extractivas para convertirse en verdaderos guardianes del medio ambiente. Sus guías ofrecen recorridos que combinan paisajes inolvidables con historias de conservación y desarrollo comunitario.

¿Cómo llegar? Desde Dagua, se toma la vía hacia El Queremal y se sigue hasta El Danubio, siempre acompañado de un guía. Este tesoro natural requiere compromiso con su cuidado.

Avistamiento de Aves Doña Dora

Rupicola Peruviana

Ubicación

Corregimiento La Elsa, km 55 antigua vía al mar Simón Bolívar.

Actividades

Caminata, interpretación ambiental, baño en cascadas y avistamiento de aves, anfibios y flora.

Duración de la experiencia

8 horas.

Servicios Incluidos

Hospedaje y alimentación.

Contacto

Elbert Sánchez
WhatsApp: 316 7996929

Finca El Descanso ofrece a sus visitantes una experiencia única de conexión con diversas especies de aves, incluyendo algunas endémicas de la región. Con instalaciones que crean diferentes ambientes, cuenta con un sendero especialmente diseñado para el avistamiento del Gallito de Roca, una de las aves más emblemáticas de Colombia.

Ideal para los amantes de la ornitología y la naturaleza, este lugar permite apreciar la belleza y diversidad de las aves del Valle del Cauca en un entorno natural incomparable. Podrás disfrutar de la deliciosa gastronomía que ofrece este acogedor lugar, atendido con esmero por sus propios dueños.

Semnornis Ramphastinus

Cascada Virgen de los Remedios

Ubicado en el PNN Farallones de Cali, este recorrido de nivel físico medio-alto te permitirá disfrutar de impresionantes vistas de los ríos San Juan y Cavas. El sendero culmina en una hermosa cascada, ofreciendo un espacio perfecto para contemplar la naturaleza y conectarte con el entorno. Además, tendrás la oportunidad de conocer la historia más antigua de la patrona de los vallecaucanos; la Virgen de los Remedios, conocida por los aborígenes del territorio como La Montañerita Cimarrona. Este lugar es ideal para los amantes de la aventura que buscan un desafío en un entorno natural privilegiado.

Ubicación

Corregimiento La Elsa, km 55 de la antigua vía al mar - Simón Bolívar.

Actividades

Caminata exigente, interpretación ambiental, baño en cascadas y avistamiento de aves.

Duración de la experiencia

6 horas.

Servicios Incluidos

Guianza - intérprete. Tarjeta de asistencia médica, bono ambiental y alimentación.

Contacto

Halcones Valle Expeditions
WhatsApp:
318 5240974
315 3434729

Cascada el Manto de la Virgen

Este recorrido, de nivel físico medio-alto, se desarrolla en el Parque Nacional Natural Farallones, donde podrás disfrutar de los ríos San Juan, Cavas y Digua, culminando en la imponente Cascada Manto de la Virgen, siendo esta una de las más altas del Valle del Cauca. Ideal para los aventureros que buscan paisajes impresionantes en plena naturaleza.

Ubicación

Vereda del Digua, km 57 antigua vía al mar Simón Bolívar.

Actividades

Caminata exigente, interpretación ambiental, baño en cascadas y avistamiento de aves.

Duración de la experiencia

6 horas.

Servicios Incluidos

Guianza – intérprete. Tarjeta de asistencia médica, bono ambiental y alimentación.

Contacto

Halcones Valle Expeditions
WhatsApp:
318 5240974
315 3434729

Ubicación

Vereda del Digua, km 57 antigua vía al mar Simón Bolívar.

Actividades

Caminata exigente, interpretación ambiental, baño en cascadas y avistamiento de aves.

Duración de la experiencia

3 horas.

Servicios Incluidos

Bono ambiental y alimentación.

Cascada La Elsa

Una visita perfecta para quienes buscan relajación en un entorno natural. La Cascada La Elsa ofrece un corto y fácil sendero con baja exigencia física, ideal para familias o principiantes. Disfruta de un refrescante baño en sus aguas cristalinas. Además, en los alrededores, podrás encontrar alimentos preparados por las cocineras locales de Anchicayá para completar tu experiencia.

Siete Charcos

Ubicado dentro del Parque Nacional Natural Farallones de Cali, el Siete Charcos es un destino ideal para quienes buscan disfrutar de piscinas naturales formadas por el río, rodeadas de impresionantes paisajes naturales. Sus cristalinas aguas y la biodiversidad del entorno lo convierten en un lugar perfecto para relajarse y conectarse con la naturaleza y el poder purificador del agua.

Ubicación

Corregimiento El Danubio, km 81 antigua vía al mar Simón Bolívar.

Actividades

Caminata, interpretación, baño en cascadas y piscinas naturales.

Duración de la experiencia

2-6 horas.

Servicios Incluidos

Ingreso – guianza, tarjeta de asistencia médica.

Contacto

Cortucan
Fredy Rebolledo
WhatsApp: 321 8872718

Ubicación

Vereda El Cauchal, antigua vía al mar Simón Bolívar.

Actividades

Caminata, interpretación, baño en cascadas y piscinas naturales.

Duración de la experiencia

6 horas.

Servicios Incluidos

Ingreso – guianza, tarjeta de asistencia médica.

Contacto

Sandra Patricia Zamorano
WhatsApp: 322 5122499

Charco La Oculta

Situado dentro del Parque Nacional Natural Farallones, el Charco La Oculta ofrece una experiencia completa de inmersión en la naturaleza. Este recorrido incluye contemplación de paisajes, caminatas por el río, baños refrescantes y la oportunidad de disfrutar de la gastronomía local. Conocido por desafiar tus límites y resistencia física, este lugar es perfecto para elevar tu conciencia y armonizar cuerpo y mente en plena naturaleza.

Ubicación

Corregimiento La Cascada, antigua vía al mar Simón Bolívar.

Actividades

Caminata exigente, interpretación ambiental, baño en cascadas y avistamiento de aves, anfibios y flora.

Servicios Incluidos

Ingreso, guianza, tarjeta de asistencia médica, alimentación.

Duración de la experiencia

8 horas.

Contacto

Dora Yorleny Sepúlveda
WhatsApp: 314 5275117
Dairon Antonio Ultima
WhatsApp: 300 2349203

Reserva Natural El Paraíso

Esta es una de las experiencias más retadoras y gratificantes de la cuenca de Anchicayá, ya que puedes realizar trekking de 7 km por la selva del Pacífico, recorriendo exigentes caminos que ahora se utilizan para el avistamiento de aves, incluyendo la exótica ave conocida como el paragüero del Pacífico (Cephalopterus penduliger). Guiado por un miembro de la comunidad local, este recorrido también te permitirá observar la rana Oophaga Lehmanni y la impresionante cascada El Anillo.

Es una experiencia única que te conecta directamente con la biodiversidad del Chocó iogeográfico.

Charco La Sirena

En el corazón de la Reserva Forestal Protectora Nacional del Río Anchicayá se encuentra el encantador Charco La Sirena, uno de los sitios más visitados de la cuenca de Anchicayá. A través de un recorrido por senderos naturales, descubrirás la magia de La Sirena y la serenidad del Charco del Amor, ofreciendo una experiencia inolvidable para los amantes de la naturaleza.

Ubicación

Corregimiento El Danubio, km 85 antigua vía al mar Simón Bolívar.

Actividades

Caminata, interpretación, baño en cascadas y piscinas naturales.

Duración de la experiencia

2-3 horas.

Servicios Incluidos

Ingreso – guianza, tarjeta de asistencia médica.

Contacto

Diego Fernando Sánchez
WhatsApp: 318 5608796

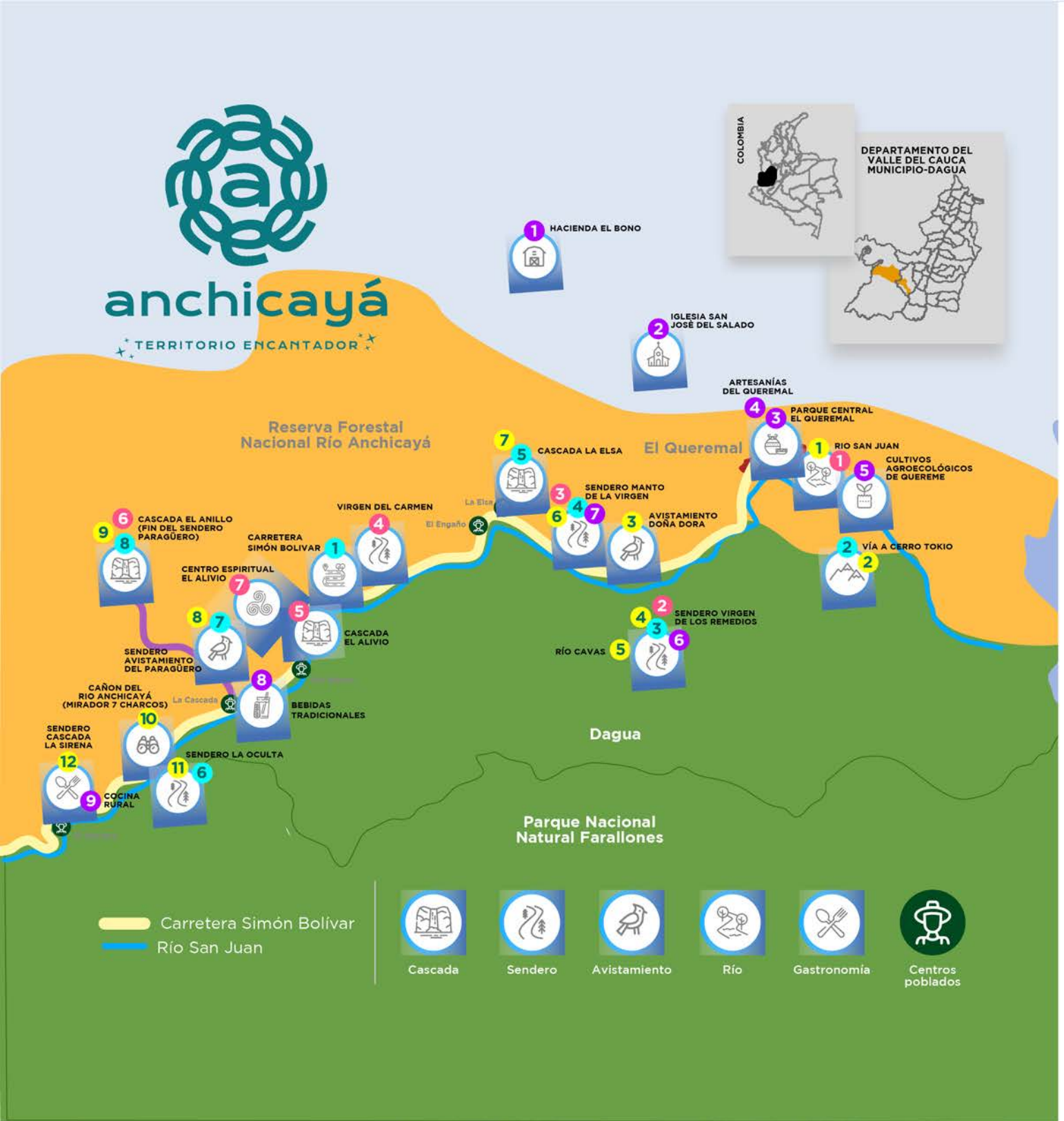

RUTA 1
BIODIVERSIDAD

1. Río San Juan
2. Vía Cerro Tokio, Avistamiento De Aves
3. Avistamiento Doña Dora: Pájaro Compás y Gallito De Roca
4. Sendero Virgen De Los Remedios: Gallito de Roca
5. Río Cavas
6. Sendero Manto De La Virgen
7. Cascada La Elsa
8. Sendero Avistamiento Del Paragüero: Pájaro Paragüero
9. Cascada El Anillo - Fin Del Sendero Paragüero
10. Cañón Del Anchicayá - Siete Charcos
11. Sendero La Oculta
12. Sendero Cascada La Sirena
13. Río Anchicayá

RUTA 2
AVENTURA

1. Carretera Simón Bolívar
2. Vía a Cerro Tokio hasta la Cumbre del Cerro
3. Sendero Virgen de los Remedios
4. Sendero Manto de la Virgen
5. Cascada la Elsa
6. Sendero La Oculta
7. Sendero Al Paragüero
8. Cascada El Anillo - Fin del Sendero Paraguero

RUTA 3
BIENESTAR

1. Río San Juan
2. Sendero Virgen de los Remedios
3. Sendero Manto de la Virgen
4. Virgen del Carmen (en El Engaño)
5. Cascada El Alivio
6. Cascada El Anillo - Fin del Sendero Paraguero
7. Centro Espiritual el Alivio

RUTA 4
TURISMO CULTURAL

1. Pan de Bono: Hacienda el Bono
2. San José del Salado: Torre Mudéjar - Patrimonio arquitectónico e histórico de Dagua
3. Parque Principal del Queremal - Monumento al Quereme
4. Artesanías de El Queremal - Parque Principal el Queremal
5. Cultivos agroecológicos de Quereme - Vía Cerro Tokio
6. Sendero Virgen de los Remedios
7. Sendero Manto de la Virgen
8. Bebidas tradicionales - Cauchal, El Placer y El Danubio
9. Cocina rural: San José del Salado, Doña Dora, Chorrera La Elsa, Sendero Manto de la Virgen, El Engaño, El Placer, Cañón del Anchicayá, El Danubio

CRÉDITOS

ALCALDÍA MUNICIPAL DE DAGUA
Karoj Villarejo - Alcaldesa

Secretaría Economía, Deporte, Recreación, Cultura Y Turismo
Yuraine Ruíz Mamian - Secretaria de Economía, Cultura y Turismo
Carlos Montoya Carmona - Enlace de Turismo Municipal
Daniela Santamaria Campo - Jefe de Comunicaciones

DESARROLLO DEL PROYECTO

CULTURA TURÍSTICA S.A.S
Equipo
Angela Peña Cortes - Gerente
Oscar Navarrete Baena - Coordinación
Andrés Martínez Ramírez - Director de proyecto
Carlos López Duarte - Diseñador Gráfico
Alison Castro - Diseñadora Gráfica
Jhon Soto - Arquitecto

TEXTOS Y CONTENIDO
Carlos Montoya Carmona

FOTOGRAFÍAS Y MATERIAL AUDIOVISUAL
Andrés Martínez Ramírez (Material audiovisual principal)
Cristian González (Andinobates bombetes - Rana Rubí)

Diagramación
Carlos López Duarte

Descubre
DAGUA
Donde la historia y la naturaleza se encuentran

ALCALDÍA MUNICIPAL DE DAGUA
DAGUA MÁGICA Y BIODIVERSA
CULTURA TURISTICA